Филиал публично-правовой компании "Роскадастр" по Москве
полное наименование органа регистрации прав

Выписка из Единого государственного реестра недвижимости об объекте недвижимости

Сведения о характеристиках объекта недвижимости

На основании запроса от 09.07.2025, поступившего на рассмотрение 09.07.2025, сообщаем, что согласно записям Единого государственного реестра недвижимости:

Раздел 1 Лист 1

| Здание |
|---|
| вид объекта недвижимости |

| Лист № 1 раздела 1 | Всего листов раздела 1: 2 | Всего разделов: 6 | Всего листов выписки: 22 |
|---|---|---|---|

| 10.07.2025г. № КУВИ-001/2025-137187868 | |
|---|---|
| Кадастровый номер: | 77:07:0005009:1051 |
| Номер кадастрового квартала: | 77:07:0005009 |
| Дата присвоения кадастрового номера: | 27.05.2012 |

| | |
|---|---|
| Ранее присвоенный государственный учетный номер: | Инвентарный номер 774/1; Условный номер 141752; Условный номер 2128102 14.02.1992 ГУП МосгорБТИ |
| Адрес: | Российская Федерация, город Москва, вн.тер.г. муниципальный округ Филевский парк, проезд Промышленный, дом 3, строение 2 |
| Площадь: | 1571.8 |
| Назначение: | Нежилое |
| Наименование: | Здание |
| Количество этажей, в том числе подземных этажей: | 2, в том числе подземных 0 |
| Материал наружных стен: | Кирпичные |
| Год ввода в эксплуатацию по завершении строительства: | 1970 |
| Год завершения строительства: | 1970 |
| Кадастровая стоимость, руб.: | 61987815.35 |
| Кадастровые номера иных объектов недвижимости, в пределах которых расположен объект недвижимости: | данные отсутствуют |
| Кадастровые номера помещений, машино-мест, расположенных в здании или сооружении: | 77:07:0005009:2275, 77:07:0005009:2276, 77:07:0005009:2277, 77:07:0005009:2278, 77:07:0005009:2279, 77:07:0005009:2280, 77:07:0005009:2281, 77:07:0005009:2282, 77:07:0005009:2283, 77:07:0005009:2284, 77:07:0005009:2285, 77:07:0005009:2286, 77:07:0005009:2287, 77:07:0005009:2288 |
| Кадастровые номера объектов недвижимости, из которых образован объект недвижимости: | данные отсутствуют |
| Кадастровые номера образованных объектов недвижимости: | данные отсутствуют |
| Сведения о включении объекта недвижимости в состав предприятия как имущественного комплекса: | данные отсутствуют |
| Сведения о включении объекта недвижимости в состав единого недвижимого комплекса: | данные отсутствуют |

| | | |
|---|---|---|
| | | |
| полное наименование должности | | инициалы, фамилия |

ДОКУМЕНТ ПОДПИСАН
ЭЛЕКТРОННОЙ ПОДПИСЬЮ
Сертификат: 009F0BDC181A023B64597F1E2579BEFB50
Владелец: ФЕДЕРАЛЬНАЯ СЛУЖБА ГОСУДАРСТВЕННОЙ РЕГИСТРАЦИИ, КАДАСТРА И КАРТОГРАФИИ
Действителен: с 02.08.2024 по 26.10.2025

| Здание |
|---|
| вид объекта недвижимости |

| Лист № 2 раздела 1 | Всего листов раздела 1: 2 | Всего разделов: 6 | Всего листов выписки: 22 |
|---|---|---|---|

| 10.07.2025г. № КУВИ-001/2025-137187868 | |
|---|---|
| Кадастровый номер: | 77:07:0005009:1051 |

| | |
|---|---|
| Виды разрешенного использования: | данные отсутствуют |
| Сведения о включении объекта недвижимости в реестр объектов культурного наследия: | данные отсутствуют |
| Сведения о кадастровом инженере: | дата завершения кадастровых работ: 14.02.2003 |
| Сведения о признании многоквартирного дома аварийным и подлежащим сносу или реконструкции и (или) о признании жилого помещения, в том числе жилого дома, непригодным для проживания: | данные отсутствуют |
| Статус записи об объекте недвижимости: | Сведения об объекте недвижимости имеют статус "актуальные, ранее учтенные" |
| Особые отметки: | Сведения, необходимые для заполнения раздела: 6 - Сведения о частях объекта недвижимости, отсутствуют. |
| Получатель выписки: | Киор Юрий Анатольевич |

| | | |
|---|---|---|
| | | |
| полное наименование должности | | инициалы, фамилия |

ДОКУМЕНТ ПОДПИСАН
ЭЛЕКТРОННОЙ ПОДПИСЬЮ
Сертификат: 009F0BDC181A023B64597F1E2579BEFB50
Владелец: ФЕДЕРАЛЬНАЯ СЛУЖБА ГОСУДАРСТВЕННОЙ РЕГИСТРАЦИИ, КАДАСТРА И КАРТОГРАФИИ
Действителен: с 02.08.2024 по 26.10.2025

Выписка из Единого государственного реестра недвижимости об объекте недвижимости

Сведения о зарегистрированных правах

| Здание |
|---|
| вид объекта недвижимости |

| Лист № 1 раздела 2 | Всего листов раздела 2: 2 | Всего разделов: 6 | Всего листов выписки: 22 |
|---|---|---|---|

| | |
|---|---|
| 10.07.2025г. № КУВИ-001/2025-137187868 | |
| Кадастровый номер: | 77:07:0005009:1051 |

| | | | |
|---|---|---|---|
| 1 | Правообладатель (правообладатели): | 1.1 | Федеральное государственное бюджетное учреждение "Дирекция по обеспечению деятельности федерального агенства по управлению государственным имуществом", ИНН: 7722467407 |
| | Сведения о возможности предоставления третьим лицам персональных данных физического лица: | 1.1.1 | данные отсутствуют |
| 2 | Вид, номер, дата и время государственной регистрации права: | 2.1 | Оперативное управление<br>77:07:0005009:1051-77/051/2021-1<br>26.03.2021 17:43:20 |
| 3 | Сведения об осуществлении государственной регистрации сделки, права без необходимого в силу закона согласия третьего лица, органа: | 3.1 | данные отсутствуют |
| 4 | Ограничение прав и обременение объекта недвижимости: | не зарегистрировано | |
| 1 | Правообладатель (правообладатели): | 1.2 | Российская Федерация |
| | Сведения о возможности предоставления третьим лицам персональных данных физического лица: | 1.2.1 | данные отсутствуют |
| 2 | Вид, номер, дата и время государственной регистрации права: | 2.2 | Собственность<br>77-77-13/005/2008-649<br>25.03.2008 00:00:00 |
| 3 | Сведения об осуществлении государственной регистрации сделки, права без необходимого в силу закона согласия третьего лица, органа: | 3.2 | данные отсутствуют |
| 4 | Ограничение прав и обременение объекта недвижимости: | не зарегистрировано | |
| 5 | Договоры участия в долевом строительстве: | не зарегистрировано | |
| 6 | Заявленные в судебном порядке права требования: | данные отсутствуют | |
| 7 | Сведения о возможности предоставления третьим лицам персональных данных физического лица | данные отсутствуют | |
| 8 | Сведения о возражении в отношении зарегистрированного права: | данные отсутствуют | |
| 9 | Сведения о наличии решения об изъятии объекта недвижимости для государственных и муниципальных нужд: | данные отсутствуют | |

ДОКУМЕНТ ПОДПИСАН
ЭЛЕКТРОННОЙ ПОДПИСЬЮ
Сертификат: 009F0BDC181A023B64597F1E2579BEFB50
Владелец: ФЕДЕРАЛЬНАЯ СЛУЖБА ГОСУДАРСТВЕННОЙ РЕГИСТРАЦИИ, КАДАСТРА И КАРТОГРАФИИ
Действителен: с 02.08.2024 по 26.10.2025

| | | |
|---|---|---|
| полное наименование должности | | инициалы, фамилия |

| Здание |
|---|
| вид объекта недвижимости |

| Лист № 2 раздела 2 | Всего листов раздела 2: 2 | Всего разделов: 6 | Всего листов выписки: 22 |
|---|---|---|---|

| | |
|---|---|
| 10.07.2025г. № КУВИ-001/2025-137187868 | |
| Кадастровый номер: | 77:07:0005009:1051 |

| | | |
|---|---|---|
| 10 | Сведения о невозможности государственной регистрации без личного участия правообладателя или его законного представителя: | данные отсутствуют |
| 11 | Правопритязания и сведения о наличии поступивших, но не рассмотренных заявлений о проведении государственной регистрации права (перехода, прекращения права), ограничения права или обременения объекта недвижимости, сделки в отношении объекта недвижимости: | отсутствуют |

| | | |
|---|---|---|
| | | |
| полное наименование должности | | инициалы, фамилия |

ДОКУМЕНТ ПОДПИСАН
ЭЛЕКТРОННОЙ ПОДПИСЬЮ
Сертификат: 009F0BDC181A023B64597F1E2579BEFB50
Владелец: ФЕДЕРАЛЬНАЯ СЛУЖБА ГОСУДАРСТВЕННОЙ РЕГИСТРАЦИИ, КАДАСТРА И КАРТОГРАФИИ
Действителен: с 02.08.2024 по 26.10.2025

Выписка из Единого государственного реестра недвижимости об объекте недвижимости

Описание местоположения объекта недвижимости

| |
|---|
| Здание |
| вид объекта недвижимости |

| | | | |
|---|---|---|---|
| Лист № 1 раздела 5 | Всего листов раздела 5: 1 | Всего разделов: 6 | Всего листов выписки: 22 |

| | |
|---|---|
| 10.07.2025г. № КУВИ-001/2025-137187868 | |
| Кадастровый номер: | 77:07:0005009:1051 |

Схема расположения объекта недвижимости (части объекта недвижимости) на земельном участке(ах)

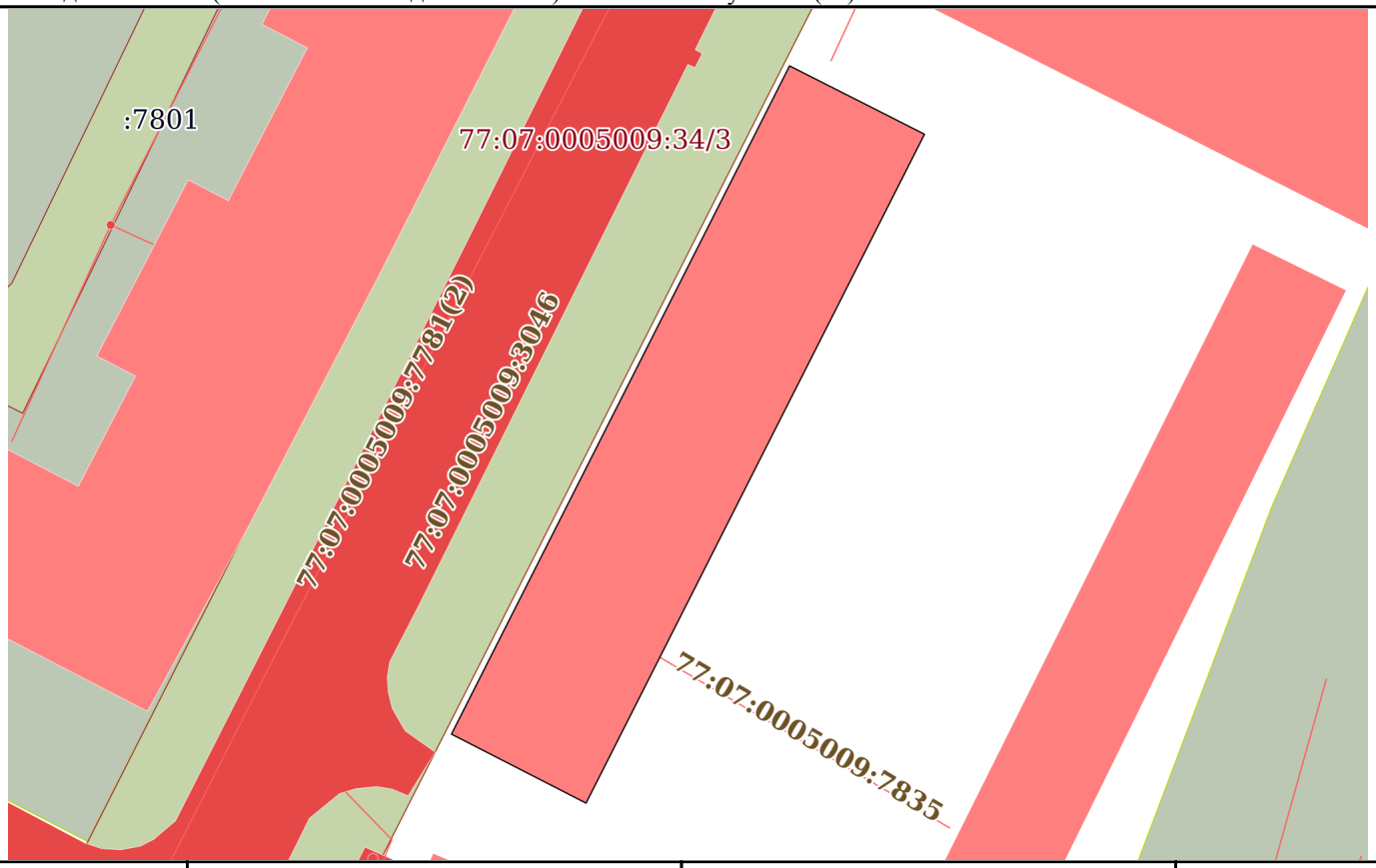


| | | | |
|---|---|---|---|
| Масштаб 1:600 | Условные обозначения: | | |

ДОКУМЕНТ ПОДПИСАН
ЭЛЕКТРОННОЙ ПОДПИСЬЮ
Сертификат: 009F0BDC181A023B64597F1E2579BEFB50
Владелец: ФЕДЕРАЛЬНАЯ СЛУЖБА ГОСУДАРСТВЕННОЙ РЕГИСТРАЦИИ, КАДАСТРА И КАРТОГРАФИИ
Действителен: с 02.08.2024 по 26.10.2025

| | | |
|---|---|---|
| | | |
| полное наименование должности | | инициалы, фамилия |

Выписка из Единого государственного реестра недвижимости об объекте недвижимости

Описание местоположения объекта недвижимости

| Здание |
|---|
| вид объекта недвижимости |

| Лист № 1 раздела 5.1 | Всего листов раздела 5.1: 2 | Всего разделов: 6 | Всего листов выписки: 22 |
|---|---|---|---|

| | |
|---|---|
| 10.07.2025г. № КУВИ-001/2025-137187868 | |
| Кадастровый номер: | 77:07:0005009:1051 |

| 1. Сведения о координатах характерных точек контура объекта недвижимости | | | | | | |
|---|---|---|---|---|---|---|
| Система координат ПМСК Москвы | | | | | | |
| Номер точки | Координаты, м | | Радиус, м | Средняя квадратическая погрешность определения координат характерных точек контура, м | Глубина, высота, м | |
| | X | Y | | | H1 | H2 |
| 1 | 2 | 3 | 4 | 5 | 6 | 7 |
| 1 | 8595.23 | 882.84 | - | - | данные отсутствуют | данные отсутствуют |
| 2 | 8589.68 | 893.67 | - | - | данные отсутствуют | данные отсутствуют |
| 3 | 8643.49 | 920.91 | - | - | данные отсутствуют | данные отсутствуют |
| 4 | 8645.66 | 916.63 | - | - | данные отсутствуют | данные отсутствуют |
| 5 | 8647.51 | 912.97 | - | - | данные отсутствуют | данные отсутствуют |
| 6 | 8648.99 | 910.05 | - | - | данные отсутствуют | данные отсутствуют |
| 1 | 8595.23 | 882.84 | - | - | данные отсутствуют | данные отсутствуют |

| 2. Сведения о предельных высоте и глубине конструктивных элементов объекта недвижимости | |
|---|---|
| Предельная глубина конструктивных элементов объекта недвижимости, м | данные отсутствуют |
| Предельная высота конструктивных элементов объекта недвижимости, м | данные отсутствуют |

| | | |
|---|---|---|
| полное наименование должности | | инициалы, фамилия |

ДОКУМЕНТ ПОДПИСАН
ЭЛЕКТРОННОЙ ПОДПИСЬЮ
Сертификат: 009F0BDC181A023B64597F1E2579BEFB50
Владелец: ФЕДЕРАЛЬНАЯ СЛУЖБА ГОСУДАРСТВЕННОЙ РЕГИСТРАЦИИ, КАДАСТРА И КАРТОГРАФИИ
Действителен: с 02.08.2024 по 26.10.2025

| Здание |
|---|
| вид объекта недвижимости |

| Лист № 2 раздела 5.1 | Всего листов раздела 5.1: 2 | Всего разделов: 6 | Всего листов выписки: 22 |
|---|---|---|---|

| | |
|---|---|
| 10.07.2025г. № КУВИ-001/2025-137187868 | |
| Кадастровый номер: | 77:07:0005009:1051 |

3. Сведения о характерных точках пересечения контура объекта недвижимости с контуром (контурами) иных зданий, сооружений, объектов незавершенного строительства

Система координат ПМСК Москвы

| Номера характерных точек контура | Координаты, м | | Средняя квадратическая погрешность определения координат характерных точек контура, м | Глубина, высота, м | | Кадастровые номера иных объектов недвижимости, с контурами которых пересекается контур данного объекта недвижимости |
|---|---|---|---|---|---|---|
| | X | Y | | H1 | H2 | |
| 1 | 2 | 3 | 4 | 5 | 6 | 7 |
| данные отсутствуют | данные отсутствуют | данные отсутствуют | данные отсутствуют | данные отсутствуют | данные отсутствуют | данные отсутствуют |

| | | |
|---|---|---|
| полное наименование должности | | инициалы, фамилия |

ДОКУМЕНТ ПОДПИСАН
ЭЛЕКТРОННОЙ ПОДПИСЬЮ
Сертификат: 009F0BDC181A023B64597F1E2579BEFB50
Владелец: ФЕДЕРАЛЬНАЯ СЛУЖБА ГОСУДАРСТВЕННОЙ РЕГИСТРАЦИИ, КАДАСТРА И КАРТОГРАФИИ
Действителен: с 02.08.2024 по 26.10.2025

Выписка из Единого государственного реестра недвижимости об объекте недвижимости

Перечень помещений, машино-мест, расположенных в здании, сооружении

| Здание |
|---|
| вид объекта недвижимости |

| Лист № 1 раздела 7 | Всего листов раздела 7: 1 | Всего разделов: 6 | Всего листов выписки: 22 |
|---|---|---|---|

| | |
|---|---|
| 10.07.2025г. № КУВИ-001/2025-137187868 | |
| Кадастровый номер: | 77:07:0005009:1051 |

| N п/п | Кадастровый номер помещения, машино-места | Номер этажа (этажей) | Обозначение (номер) помещения, машино-места на поэтажном плане | Назначение помещения | Вид разрешенного использования | Площадь, м2 |
|---|---|---|---|---|---|---|
| 1 | 77:07:0005009:2275 | 1 | 2128102/0001 | Нежилое | данные отсутствуют | 182.9 |
| 2 | 77:07:0005009:2276 | 1 | 2128102/0002 | Нежилое | данные отсутствуют | 26.5 |
| 3 | 77:07:0005009:2277 | 1 | 2128102/0003 | Нежилое | данные отсутствуют | 54.2 |
| 4 | 77:07:0005009:2278 | 1 | 2128102/0004 | Нежилое | данные отсутствуют | 16.3 |
| 5 | 77:07:0005009:2279 | 1 | 2128102/0005 | Нежилое | данные отсутствуют | 12.2 |
| 6 | 77:07:0005009:2280 | 1 | 2128102/0006 | Нежилое | данные отсутствуют | 3.8 |
| 7 | 77:07:0005009:2281 | 1 | 2128102/0007 | Нежилое | данные отсутствуют | 45.5 |
| 8 | 77:07:0005009:2282 | 1 | 2128102/0008 | Нежилое | данные отсутствуют | 193.9 |
| 9 | 77:07:0005009:2283 | 1 | 2128102/0009 | Нежилое | данные отсутствуют | 154.6 |
| 10 | 77:07:0005009:2284 | 1 | 2128102/0010 | Нежилое | данные отсутствуют | 42.1 |
| 11 | 77:07:0005009:2285 | 1 | 2128102/0011 | Нежилое | данные отсутствуют | 43.2 |
| 12 | 77:07:0005009:2286 | 2 | 2128102/0012 | Нежилое | данные отсутствуют | 670.3 |
| 13 | 77:07:0005009:2287 | 0 | 2128102/0013 | Нежилое | данные отсутствуют | 64.8 |
| 14 | 77:07:0005009:2288 | 0 | 2128102/0014 | Нежилое | данные отсутствуют | 61.5 |

| | | |
|---|---|---|
| полное наименование должности | | инициалы, фамилия |

ДОКУМЕНТ ПОДПИСАН
ЭЛЕКТРОННОЙ ПОДПИСЬЮ
Сертификат: 009F0BDC181A023B64597F1E2579BEFB50
Владелец: ФЕДЕРАЛЬНАЯ СЛУЖБА ГОСУДАРСТВЕННОЙ РЕГИСТРАЦИИ, КАДАСТРА И КАРТОГРАФИИ
Действителен: с 02.08.2024 по 26.10.2025

Выписка из Единого государственного реестра недвижимости об объекте недвижимости

План расположения помещения, машино-места на этаже (плане этажа)

| Здание |
|---|
| вид объекта недвижимости |

| Лист № 1 раздела 8 | Всего листов раздела 8: 14 | Всего разделов: 6 | Всего листов выписки: 22 |
|---|---|---|---|

| | |
|---|---|
| 10.07.2025г. № КУВИ-001/2025-137187868 | |
| Кадастровый номер: 77:07:0005009:1051 | Номер этажа (этажей): 1 |

**ПОЭТАЖНЫЙ ПЛАН**

по адресу: Промышленный проезд
наименование ул. (просп., бульв. и т.д.)

домовл.(вл.)_____ дом 3
нужное подчеркнуть

корпус_____ строение (сооружение) 2
нужное подчеркнуть

квартал № 774 Западного АО г.Москвы

## 1 этаж

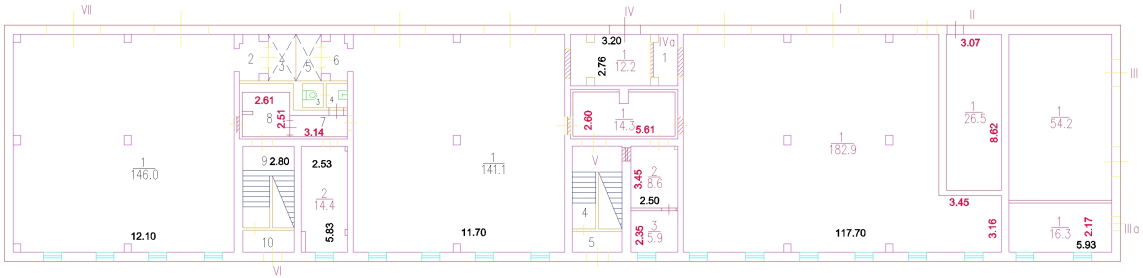


Масштаб 1:200

Разрешение на произведенное переоборудование
В кварт. пом. № I(1) II(1) IIIa(1) IV(1) IVa(1) IV(2-8,7)
Территориальному бюро технической инвентаризации не предоставлено
"14" февраля 2003 г.
Исполнитель_____
Проверил_____

Масштаб 1

| | | |
|---|---|---|
| полное наименование должности | | инициалы, фамилия |

ДОКУМЕНТ ПОДПИСАН
ЭЛЕКТРОННОЙ ПОДПИСЬЮ
Сертификат: 009F0BDC181A023B64597F1E2579BEFB50
Владелец: ФЕДЕРАЛЬНАЯ СЛУЖБА ГОСУДАРСТВЕННОЙ РЕГИСТРАЦИИ, КАДАСТРА И КАРТОГРАФИИ
Действителен: с 02.08.2024 по 26.10.2025

| Здание |
|---|
| вид объекта недвижимости |

| Лист № 2 раздела 8 | Всего листов раздела 8: 14 | Всего разделов: 6 | Всего листов выписки: 22 |
|---|---|---|---|

10.07.2025г. № КУВИ-001/2025-137187868

| Кадастровый номер: 77:07:0005009:1051 | Номер этажа (этажей): 1 |
|---|---|

## ПОЭТАЖНЫЙ ПЛАН

по адресу: Промышленный проезд
наименование ул. (просп., бульв. и т.д.)

домовл.(вл.)_____ дом 3
нужное подчеркнуть

корпус_____ строение (сооружение) 2
нужное подчеркнуть

квартал № 774 Западного АО г.Москвы

### 1 этаж

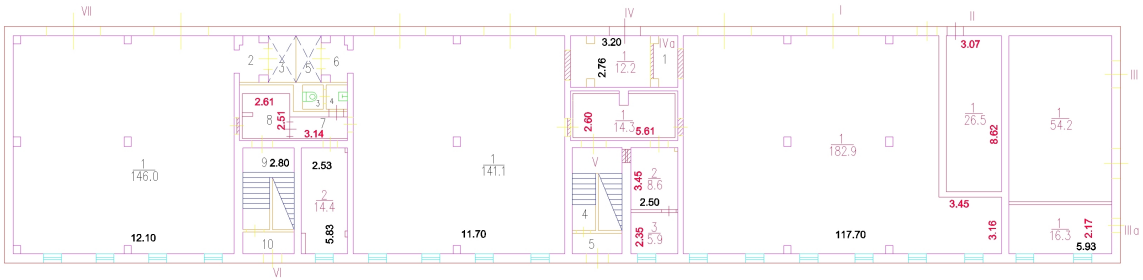


Масштаб 1:200

Разрешение на произведенное переоборудование
В квартире/помещении № I(1) II(1) IIk(1) IIIa(1) IVc(1) IVa(1) IV(2,7)
Территориальному бюро технической инвентаризации не предоставлено
"14" февраля 2003 г.
Исполнитель_____
Проверил_____

Масштаб 1

| | | |
|---|---|---|
| полное наименование должности | | инициалы, фамилия |

ДОКУМЕНТ ПОДПИСАН
ЭЛЕКТРОННОЙ ПОДПИСЬЮ
Сертификат: 009F0BDC181A023B64597F1E2579BEFB50
Владелец: ФЕДЕРАЛЬНАЯ СЛУЖБА ГОСУДАРСТВЕННОЙ РЕГИСТРАЦИИ, КАДАСТРА И КАРТОГРАФИИ
Действителен: с 02.08.2024 по 26.10.2025

| Здание |
|---|
| вид объекта недвижимости |

| Лист № 3 раздела 8 | Всего листов раздела 8: 14 | Всего разделов: 6 | Всего листов выписки: 22 |
|---|---|---|---|

10.07.2025г. № КУВИ-001/2025-137187868

| Кадастровый номер: 77:07:0005009:1051 | Номер этажа (этажей): 1 |
|---|---|

## ПОЭТАЖНЫЙ ПЛАН

по адресу: Промышленный проезд
наименование ул. (просп., бульв. и т.д.)

домовл.(вл.)_____ дом 3
нужное подчеркнуть

корпус_____ строение (сооружение) 2
нужное подчеркнуть

квартал № 774 Западного АО г.Москвы

### 1 этаж

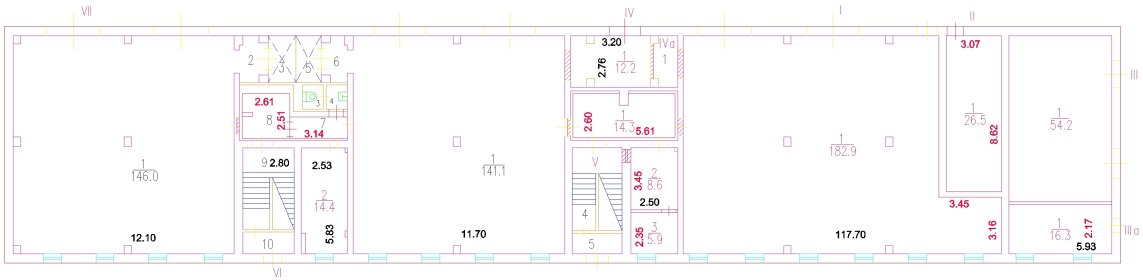


Масштаб 1:200

Разрешение на произведенное переоборудование
В квартире/помещении № I(1) II(1) IIk(1) IIIa(1) IV(1) IVa(1) IV(2a?)
Территориальному бюро технической инвентаризации не предоставлено
"14" февраля 2003 г.
Исполнитель_____
Проверил_____

Масштаб 1

| | | |
|---|---|---|
| полное наименование должности | | инициалы, фамилия |

ДОКУМЕНТ ПОДПИСАН
ЭЛЕКТРОННОЙ ПОДПИСЬЮ
Сертификат: 009F0BDC181A023B64597F1E2579BEFB50
Владелец: ФЕДЕРАЛЬНАЯ СЛУЖБА ГОСУДАРСТВЕННОЙ РЕГИСТРАЦИИ, КАДАСТРА И КАРТОГРАФИИ
Действителен: с 02.08.2024 по 26.10.2025

| Здание |
|---|
| вид объекта недвижимости |

| Лист № 4 раздела 8 | Всего листов раздела 8: 14 | Всего разделов: 6 | Всего листов выписки: 22 |
|---|---|---|---|

10.07.2025г. № КУВИ-001/2025-137187868

| Кадастровый номер: 77:07:0005009:1051 | Номер этажа (этажей): 1 |
|---|---|

## ПОЭТАЖНЫЙ ПЛАН

по адресу: Промышленный проезд
наименование ул. (просп., бульв. и т.д.)

домовл.(вл.)_____ дом 3
нужное подчеркнуть

корпус_____ строение (сооружение) 2
нужное подчеркнуть

квартал № 774 Западного АО г.Москвы

### 1 этаж

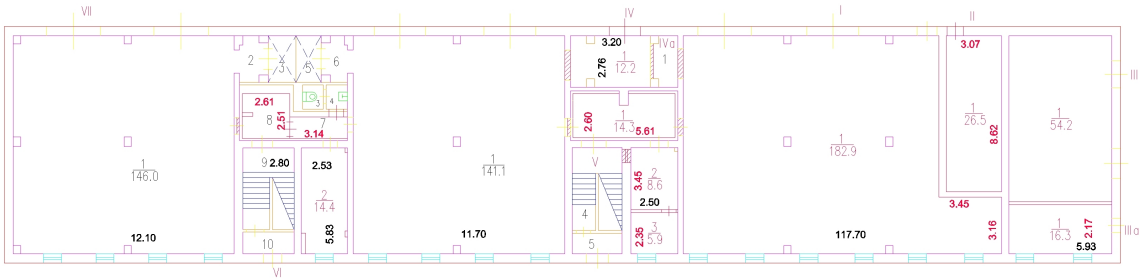


Масштаб 1:200

Разрешение на произведенное переоборудование
В квартире/помещении № I(1) II(1) IIk(1) IIIa(1) IV(1) IVa(1) IV(2,3)
Территориальному бюро технической инвентаризации не предоставлено
"14" февраля 2003 г.
Исполнитель_____
Проверил_____

Масштаб 1

| | | |
|---|---|---|
| полное наименование должности | | инициалы, фамилия |

ДОКУМЕНТ ПОДПИСАН
ЭЛЕКТРОННОЙ ПОДПИСЬЮ
Сертификат: 009F0BDC181A023B64597F1E2579BEFB50
Владелец: ФЕДЕРАЛЬНАЯ СЛУЖБА ГОСУДАРСТВЕННОЙ РЕГИСТРАЦИИ, КАДАСТРА И КАРТОГРАФИИ
Действителен: с 02.08.2024 по 26.10.2025

| Здание |
|---|
| вид объекта недвижимости |

| Лист № 5 раздела 8 | Всего листов раздела 8: 14 | Всего разделов: 6 | Всего листов выписки: 22 |
|---|---|---|---|

10.07.2025г. № КУВИ-001/2025-137187868

| Кадастровый номер: 77:07:0005009:1051 | Номер этажа (этажей): 1 |
|---|---|

**ПОЭТАЖНЫЙ ПЛАН**

по адресу: Промышленный проезд
наименование ул. (просп., бульв. и т.д.)

домовл.(вл.)_____ дом 3
нужное подчеркнуть

корпус_____ строение (сооружение) 2
нужное подчеркнуть

квартал № 774 Западного АО г.Москвы

## 1 этаж

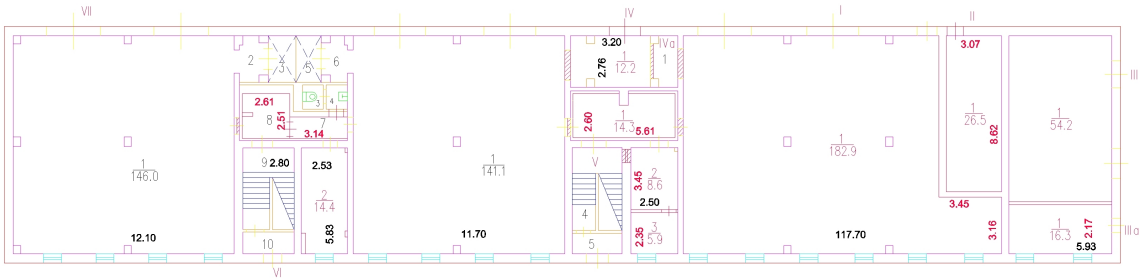


Масштаб 1:200

Разрешение на произведенное переоборудование
В квартире/помещении № I(1) II(1) IIk(1) IIIa(1) IV(1) IVa(1) IV(2,3)
Территориальному бюро технической инвентаризации не предоставлено
"14" февраля 2003 г.
Исполнитель_____
Проверил_____

Масштаб 1

| | | |
|---|---|---|
| полное наименование должности | | инициалы, фамилия |

ДОКУМЕНТ ПОДПИСАН
ЭЛЕКТРОННОЙ ПОДПИСЬЮ
Сертификат: 009F0BDC181A023B64597F1E2579BEFB50
Владелец: ФЕДЕРАЛЬНАЯ СЛУЖБА ГОСУДАРСТВЕННОЙ РЕГИСТРАЦИИ, КАДАСТРА И КАРТОГРАФИИ
Действителен: с 02.08.2024 по 26.10.2025

| Здание |
|---|
| вид объекта недвижимости |

| Лист № 6 раздела 8 | Всего листов раздела 8: 14 | Всего разделов: 6 | Всего листов выписки: 22 |
|---|---|---|---|

10.07.2025г. № КУВИ-001/2025-137187868

| Кадастровый номер: 77:07:0005009:1051 | Номер этажа (этажей): 1 |
|---|---|

**ПОЭТАЖНЫЙ ПЛАН**

по адресу: Промышленный проезд
наименование ул. (просп., бульв. и т.д.)

домовл.(вл.)_____ дом 3
нужное подчеркнуть

корпус_____ строение (сооружение) 2
нужное подчеркнуть

квартал № 774 Западного АО г.Москвы

1 этаж

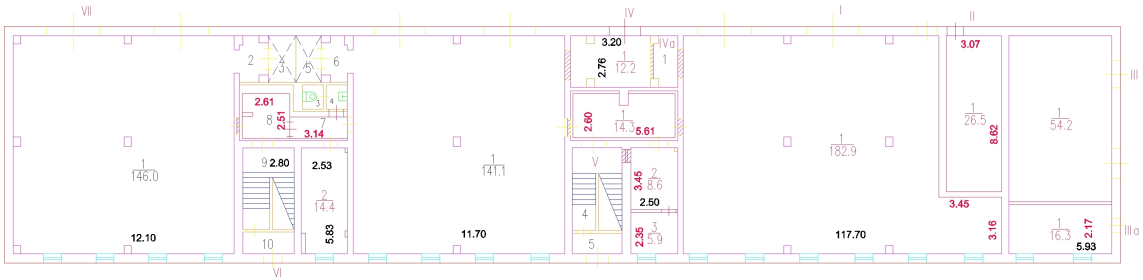


Масштаб 1:200

Разрешение на произведенное переоборудование
В квартире/помещении № I(1) II(1) IIk(1) IIIa(1) IVc(1) IVa(1) IV(2,3)
Территориальному бюро технической инвентаризации не предоставлено
"14" февраля 2003 г.
Исполнитель_____
Проверил_____

Масштаб 1

| | | |
|---|---|---|
| полное наименование должности | | инициалы, фамилия |

ДОКУМЕНТ ПОДПИСАН
ЭЛЕКТРОННОЙ ПОДПИСЬЮ
Сертификат: 009F0BDC181A023B64597F1E2579BEFB50
Владелец: ФЕДЕРАЛЬНАЯ СЛУЖБА ГОСУДАРСТВЕННОЙ РЕГИСТРАЦИИ, КАДАСТРА И КАРТОГРАФИИ
Действителен: с 02.08.2024 по 26.10.2025

| Здание |
|---|
| вид объекта недвижимости |

| Лист № 7 раздела 8 | Всего листов раздела 8: 14 | Всего разделов: 6 | Всего листов выписки: 22 |
|---|---|---|---|

10.07.2025г. № КУВИ-001/2025-137187868

| Кадастровый номер: 77:07:0005009:1051 | Номер этажа (этажей): 1 |
|---|---|

## ПОЭТАЖНЫЙ ПЛАН

по адресу: Промышленный проезд
наименование ул. (просп., бульв. и т.д.)

домовл.(вл.)_____ дом 3
нужное подчеркнуть

корпус_____ строение (сооружение) 2
нужное подчеркнуть

квартал № 774 Западного АО г.Москвы

### 1 этаж

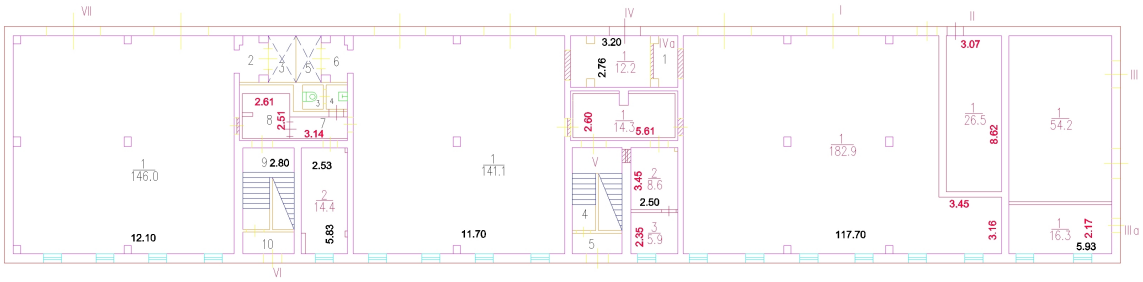


Масштаб 1:200

Разрешение на произведенное переоборудование
В квартире/помещении № I(1) II(1) IIk(1) IIIa(1) IVt(1) IVa(1) IV(2,3)
Территориальному бюро технической инвентаризации не предоставлено
"14" февраля 2003 г.
Исполнитель_____
Проверил_____

Масштаб 1

| | | |
|---|---|---|
| полное наименование должности | | инициалы, фамилия |

ДОКУМЕНТ ПОДПИСАН
ЭЛЕКТРОННОЙ ПОДПИСЬЮ
Сертификат: 009F0BDC181A023B64597F1E2579BEFB50
Владелец: ФЕДЕРАЛЬНАЯ СЛУЖБА ГОСУДАРСТВЕННОЙ РЕГИСТРАЦИИ, КАДАСТРА И КАРТОГРАФИИ
Действителен: с 02.08.2024 по 26.10.2025

| Здание |
|---|
| вид объекта недвижимости |

| Лист № 8 раздела 8 | Всего листов раздела 8: 14 | Всего разделов: 6 | Всего листов выписки: 22 |
|---|---|---|---|

10.07.2025г. № КУВИ-001/2025-137187868

| Кадастровый номер: 77:07:0005009:1051 | Номер этажа (этажей): 1 |
|---|---|

## ПОЭТАЖНЫЙ ПЛАН

по адресу: Промышленный проезд
наименование ул. (просп., бульв. и т.д.)

домовл.(вл.)_____ дом 3
нужное подчеркнуть

корпус_____ строение (сооружение) 2
нужное подчеркнуть

квартал № 774 Западного АО г.Москвы

### 1 этаж

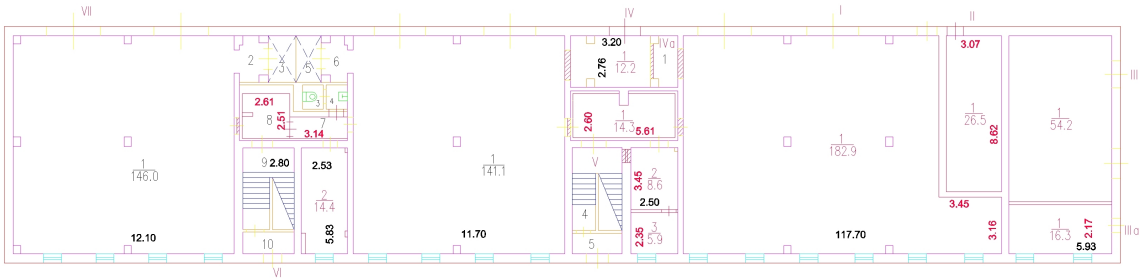


Масштаб 1:200

Разрешение на произведенное переоборудование
В квартире/помещении № I(1) II(1) IIk(1) IIIa(1) IVk(1) IVa(1) IV(2,3)
Территориальному бюро технической инвентаризации не предоставлено
"14" февраля 2003 г.
Исполнитель_____
Проверил_____

Масштаб 1

| | | |
|---|---|---|
| полное наименование должности | | инициалы, фамилия |

ДОКУМЕНТ ПОДПИСАН
ЭЛЕКТРОННОЙ ПОДПИСЬЮ
Сертификат: 009F0BDC181A023B64597F1E2579BEFB50
Владелец: ФЕДЕРАЛЬНАЯ СЛУЖБА ГОСУДАРСТВЕННОЙ РЕГИСТРАЦИИ, КАДАСТРА И КАРТОГРАФИИ
Действителен: с 02.08.2024 по 26.10.2025

| Здание |
|---|
| вид объекта недвижимости |

| Лист № 9 раздела 8 | Всего листов раздела 8: 14 | Всего разделов: 6 | Всего листов выписки: 22 |
|---|---|---|---|

10.07.2025г. № КУВИ-001/2025-137187868

| Кадастровый номер: 77:07:0005009:1051 | Номер этажа (этажей): 1 |
|---|---|

ПОЭТАЖНЫЙ ПЛАН

по адресу: Промышленный проезд
наименование ул. (просп., бульв. и т.д.)

домовл.(вл.)_____ дом 3
нужное подчеркнуть

корпус_____ строение (сооружение) 2
нужное подчеркнуть

квартал № 774 Западного АО г.Москвы

1 этаж

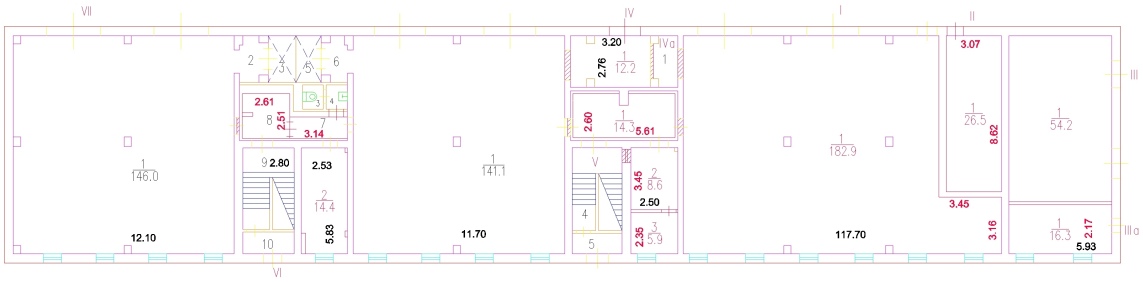


Масштаб 1:200

Разрешение на произведенное переоборудование
В квартире/помещении № I(1) II(1) IIk(1) IIIa(1) IV(1) IVa(1) IV(2a)
Территориальному бюро технической инвентаризации не предоставлено
"14" февраля 2003 г.
Исполнитель_____
Проверил_____

Масштаб 1

| | | |
|---|---|---|
| полное наименование должности | | инициалы, фамилия |

ДОКУМЕНТ ПОДПИСАН
ЭЛЕКТРОННОЙ ПОДПИСЬЮ
Сертификат: 009F0BDC181A023B64597F1E2579BEFB50
Владелец: ФЕДЕРАЛЬНАЯ СЛУЖБА ГОСУДАРСТВЕННОЙ РЕГИСТРАЦИИ, КАДАСТРА И КАРТОГРАФИИ
Действителен: с 02.08.2024 по 26.10.2025

| Здание |
|---|
| вид объекта недвижимости |

| Лист № 10 раздела 8 | Всего листов раздела 8: 14 | Всего разделов: 6 | Всего листов выписки: 22 |
|---|---|---|---|

| 10.07.2025г. № КУВИ-001/2025-137187868 | |
|---|---|
| Кадастровый номер: 77:07:0005009:1051 | Номер этажа (этажей): 1 |

антресоль 1 этажа
Промышленный проезд д.3 стр.2

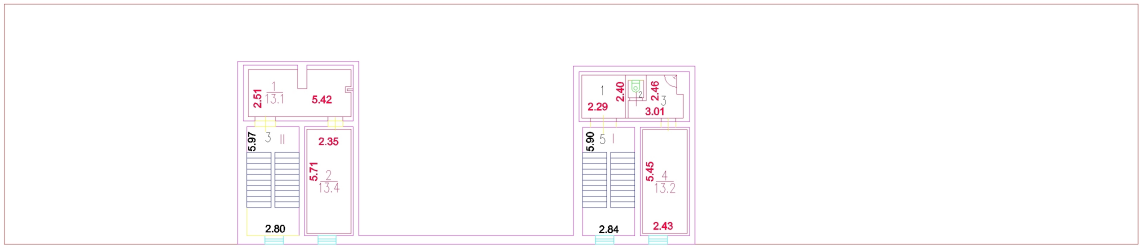


Масштаб 1:200

Разрешение на произведенное переоборудование
В квартире/пом. № I(1;2;3;4) II(1;2)
Территориальному бюро технической инвентаризации не предоставлено
"14" февраля 2003 г.
Исполнитель
Проверил

Масштаб 1

| | | |
|---|---|---|
| полное наименование должности | | инициалы, фамилия |

ДОКУМЕНТ ПОДПИСАН
ЭЛЕКТРОННОЙ ПОДПИСЬЮ
Сертификат: 009F0BDC181A023B64597F1E2579BEFB50
Владелец: ФЕДЕРАЛЬНАЯ СЛУЖБА ГОСУДАРСТВЕННОЙ РЕГИСТРАЦИИ, КАДАСТРА И КАРТОГРАФИИ
Действителен: с 02.08.2024 по 26.10.2025

| Здание |
|---|
| вид объекта недвижимости |

| Лист № 11 раздела 8 | Всего листов раздела 8: 14 | Всего разделов: 6 | Всего листов выписки: 22 |
|---|---|---|---|

| 10.07.2025г. № КУВИ-001/2025-137187868 | |
|---|---|
| Кадастровый номер: 77:07:0005009:1051 | Номер этажа (этажей): 1 |

антресоль 1 этажа
Промышленный проезд д.3 стр.2

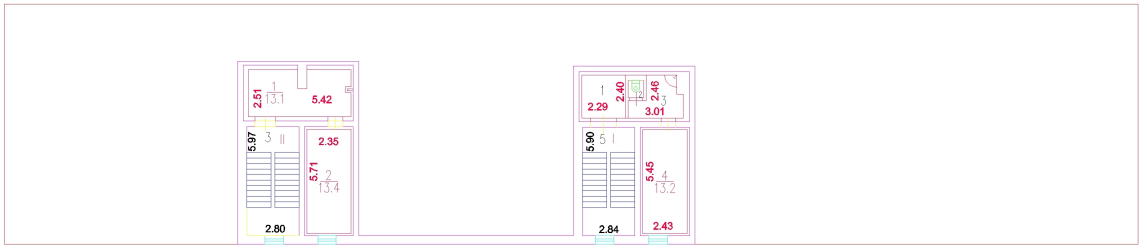


Масштаб 1:200

Разрешение на произведенное переоборудование
В кварт./пом. № I(1;2;3;4) II(1;2)
Территориальному бюро технической инвентаризации не предоставлено
" 14 " февраля 2003 г.
Исполнитель
Проверил

Масштаб 1

| | | |
|---|---|---|
| полное наименование должности | | инициалы, фамилия |

ДОКУМЕНТ ПОДПИСАН
ЭЛЕКТРОННОЙ ПОДПИСЬЮ
Сертификат: 009F0BDC181A023B64597F1E2579BEFB50
Владелец: ФЕДЕРАЛЬНАЯ СЛУЖБА ГОСУДАРСТВЕННОЙ РЕГИСТРАЦИИ, КАДАСТРА И КАРТОГРАФИИ
Действителен: с 02.08.2024 по 26.10.2025

| Здание |
|---|
| вид объекта недвижимости |

| Лист № 12 раздела 8 | Всего листов раздела 8: 14 | Всего разделов: 6 | Всего листов выписки: 22 |
|---|---|---|---|

| | |
|---|---|
| 10.07.2025г. № КУВИ-001/2025-137187868 | |
| Кадастровый номер: 77:07:0005009:1051 | Номер этажа (этажей): 2 |

2 этаж
Промышленный проезд д.3 стр.2

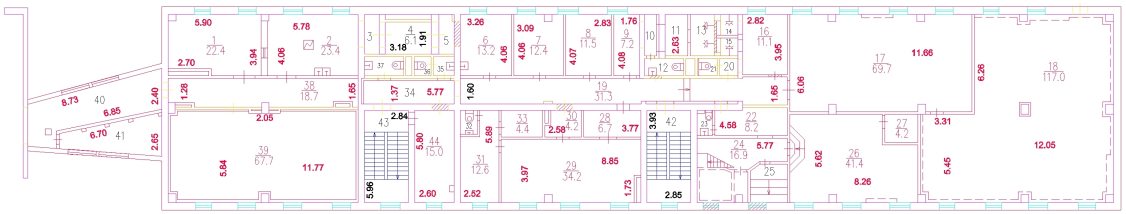

Масштаб 1:200

Разрешение на произведенное переоборудование
В квартире/помещении № 1(1-2541) 1(2-17)
Территориальному бюро технической инвентаризации не предоставлено
" 14 " февраля 2003 г.
Исполнитель
Проверил

Поэтажный план составлен по состоянию на
" 14 " февраля 2003 г.
П/план снял Ткачев Н.И.
Проверил Сорочкина М.Г.
" 21 " апреля 2011 г.

Масштаб 1

| | | |
|---|---|---|
| полное наименование должности | | инициалы, фамилия |

ДОКУМЕНТ ПОДПИСАН
ЭЛЕКТРОННОЙ ПОДПИСЬЮ
Сертификат: 009F0BDC181A023B64597F1E2579BEFB50
Владелец: ФЕДЕРАЛЬНАЯ СЛУЖБА ГОСУДАРСТВЕННОЙ РЕГИСТРАЦИИ, КАДАСТРА И КАРТОГРАФИИ
Действителен: с 02.08.2024 по 26.10.2025

| Здание |
|---|
| вид объекта недвижимости |

| Лист № 13 раздела 8 | Всего листов раздела 8: 14 | Всего разделов: 6 | Всего листов выписки: 22 |
|---|---|---|---|

| 10.07.2025г. № КУВИ-001/2025-137187868 | |
|---|---|
| Кадастровый номер: 77:07:0005009:1051 | Номер этажа (этажей): 0 |

надстройка
Промышленный проезд д.3 стр.2

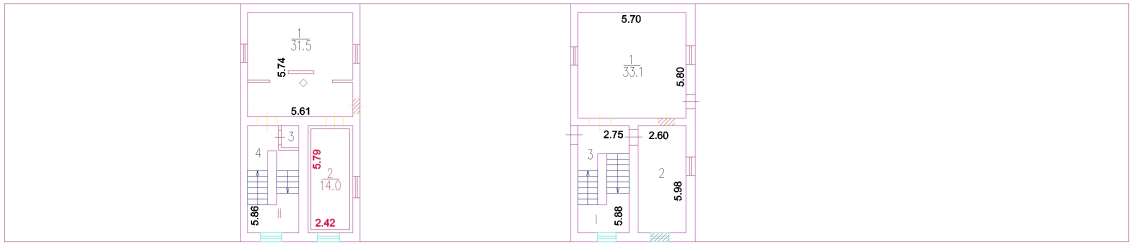


Масштаб 1:200

Переналожен камерально

Разрешение на произведенное переоборудование
В кварт./пом. № I(1;2;3;4) II(1;2)
Территориальному бюро технической инвентаризации не предоставлено
" 14 " февраля 2003 г.
Исполнитель
Проверил

Поэтажный план составлен по состоянию на
" 14 " февраля 2003 г.
П/план снял Ткачев Н.И.
Проверил Сорочкина М.Г.
" 19 " апреля 2011 г.

Масштаб 1

| | | |
|---|---|---|
| полное наименование должности | | инициалы, фамилия |

ДОКУМЕНТ ПОДПИСАН
ЭЛЕКТРОННОЙ ПОДПИСЬЮ
Сертификат: 009F0BDC181A023B64597F1E2579BEFB50
Владелец: ФЕДЕРАЛЬНАЯ СЛУЖБА ГОСУДАРСТВЕННОЙ РЕГИСТРАЦИИ, КАДАСТРА И КАРТОГРАФИИ
Действителен: с 02.08.2024 по 26.10.2025

| Здание |
|---|
| вид объекта недвижимости |

| Лист № 14 раздела 8 | Всего листов раздела 8: 14 | Всего разделов: 6 | Всего листов выписки: 22 |
|---|---|---|---|

| 10.07.2025г. № КУВИ-001/2025-137187868 | |
|---|---|
| Кадастровый номер: 77:07:0005009:1051 | Номер этажа (этажей): 0 |

надстройка
Промышленный проезд д.3 стр.2

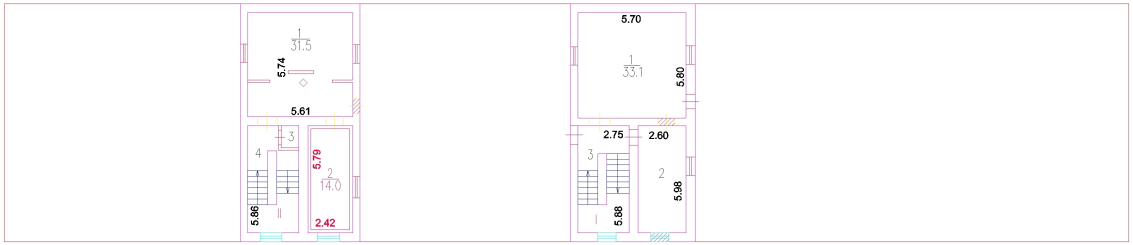


Масштаб 1:200

Переналожен камерально

Разрешение на произведенное переоборудование
В кварт./пом. № I(1;2;3;4) II(1;2)
Территориальному бюро технической инвентаризации не предоставлено
" 14 " февраля 2003 г.
Исполнитель
Проверил

Поэтажный план составлен по состоянию на
" 14 " февраля 2003 г.
П/план снял Ткачев Н.И.
Проверил Сорочкина М.Г.
" 19 " апреля 2011 г.

Масштаб 1

| | | |
|---|---|---|
| полное наименование должности | | инициалы, фамилия |

ДОКУМЕНТ ПОДПИСАН
ЭЛЕКТРОННОЙ ПОДПИСЬЮ
Сертификат: 009F0BDC181A023B64597F1E2579BEFB50
Владелец: ФЕДЕРАЛЬНАЯ СЛУЖБА ГОСУДАРСТВЕННОЙ РЕГИСТРАЦИИ, КАДАСТРА И КАРТОГРАФИИ
Действителен: с 02.08.2024 по 26.10.2025